Prefixo do Posto LD - 2

6ª Zona Hidrográfica Nome do posto USINA BAIRRO

FICHA DESCRITIVA DE POSTO FLUVIOMÉTRICO

Rio DA USINA Município SÃO JOSÉ DO BARREIRO

Sub.-Bacia e Bacia RIBEIRÃO DO BARREIRO

Coordenadas Geográficas: Lat. 22°39' Long: 44°34'

Estabelecido em: 26/08/60 Por: J. Vieira

Início das Obervações 27/08/60 Área de Drenagem Km²

Localização do Posto O pôsto está na chegada da usina que fica a .... km da cidade.

Acessibilidade e meios de Comunicação Via Dutra até km 206,600 - Entra-se à direita na antiga São Paulo/Rio, passando por Silveiras, Areias e São José do Barreiro.

ESCALA

Localização e Descrição Está instalada a jusante da casa de fôrça, em tijolos, vigas braçadeiras e placas limnimétricas.

Número de Lances 3 (três) Comprimento dos Lances 1º) 1,000m

Comprimento Total 3,000 m. 2º) 1,000m

3º) 1,000m

4º)

Altitude do Zero da Escala 629,263 m. 5º)

RR. N.N. — Cotas, Detalhes Construtivos, Localização.

RN 1 = 632,050m - Está na frente do 3º lance 3,50m.

RN 2 = Está do lado direito do RN 2 8,20m, lado jusante.

Marco de concreto com parafusos chumbados.

LINÍGRAFO

Instalado em: Por:

Fabricante Tipo Nº

Localização em relação à escala

Data do início das observações

MOD. F-1

LD - 2

LEVANTAMENTO DA SECÇÃO TRANSVERSAL DO RIO (Secção de Medição)

— 3/9/70 —

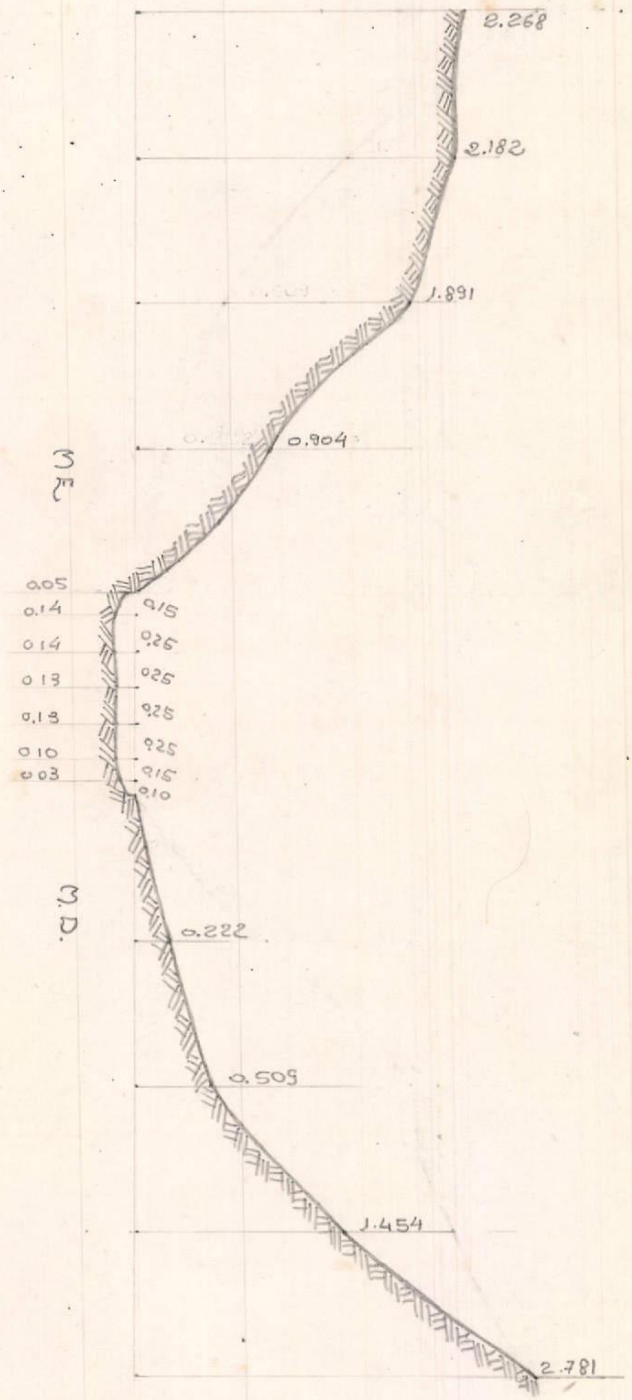

REGUA — 0,33

ESC. HOR. 1.50

VERT. 1.50

D.A.E.E.-C.P.A.

PREFIXO DO POSTO 1D - 2

6ª ZONA HIDROGRÁFICA

LOCAL BAIRRO DA USINA

CROQUIS DE LOCALIZAÇÃO DO POSTO
(LINÍGRAFO, ESCALAS, R.R.N.N., SECÇÃO DE MEDIÇÃO, CONTROLE)

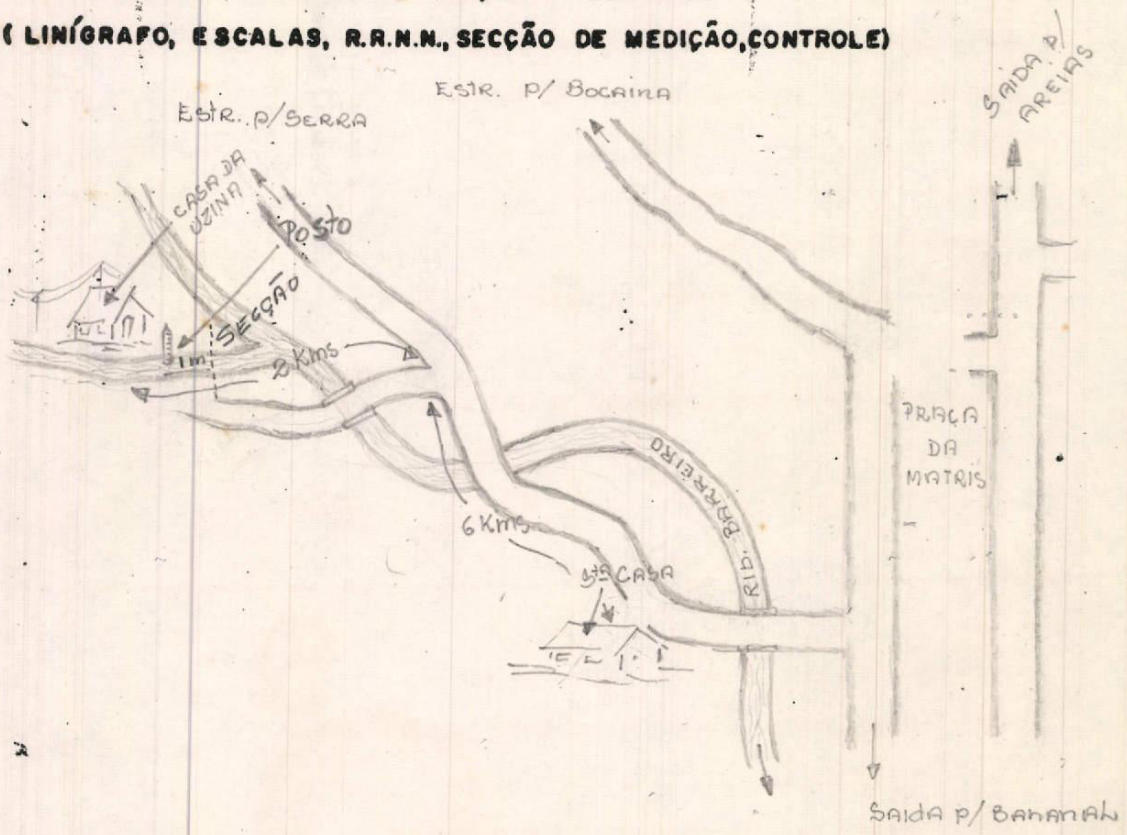
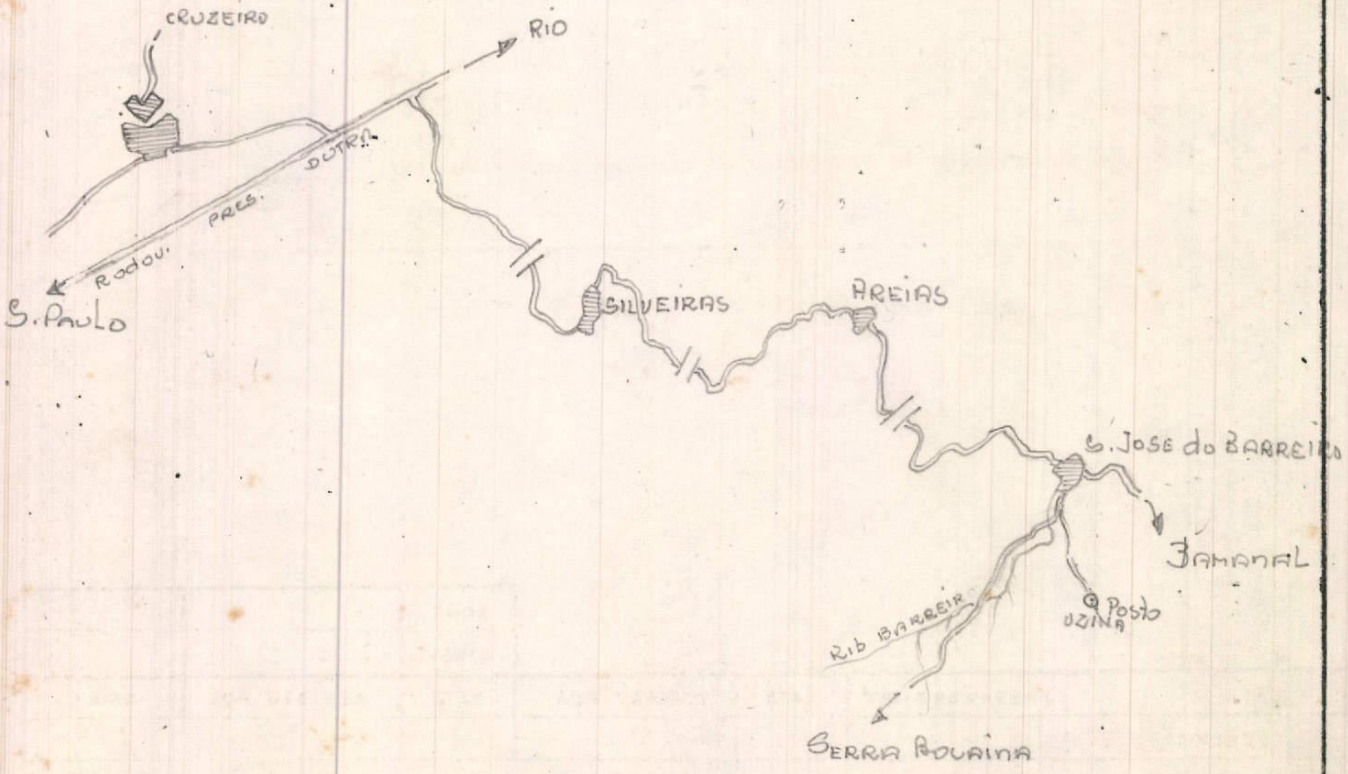
LOCALIZAÇÃO GERAL DO POSTO
(EM RELAÇÃO A CIDADES, AFLUENTES, ESTRADAS, E.TC.)